PUSH LIST — SERVIÇOS DAENG

ASU Jundiaí (26001) | OTZ Engenharia × Messer Gases for Life

P-DE-E-179-CIV18-000-003 — AIR SEPARATION UNIT MASTER PLAN | Terraplanagem — Planta | OTZ PGE | Aprov.: RNW | 19/08/25

Ref: CLM-216 | Contratada: Andrade e Rocha (DAENG) | Gerenciadora: OTZ Engenharia — GPLAN | Levantamento: 02/07/2026

Elaborado por: Caio Sergio Bento da Silva & Ilson do Santos Azevedo | **REV3 — 08/07/2026**

◆ INDICADORES GERAIS

49	225	48	177	−12.0 pp
LOCAIS / CARDS	TOTAL ATIVIDADES	CONCLUÍDAS	PENDENTES	DEFASAGEM CURVA-S
				Prev: 33% / Real: 21.3%

4	12.0 atv/dia	25/07/2026
DIAS EM ABERTO	VELOCIDADE	DATA DE TENDÊNCIA
úteis desde 04/07/2026		⚠ 7 d.úteis após prazo | ritmo: 12.0 atv/dia

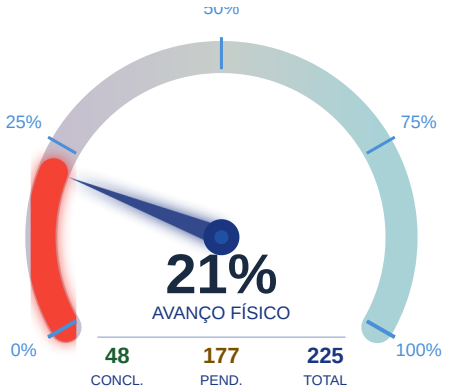

◆ ATIVIDADES POR DISCIPLINA — AVANÇO FÍSICO

Macrodrenagem	27/114	24%
Geral / 5S	3/41	7%
Terraplanagem	3/29	10%
Plantio de Grama	13/26	50%
CFTV	2/15	13%

◆ CURVA-S — PREVISTO × REALIZADO

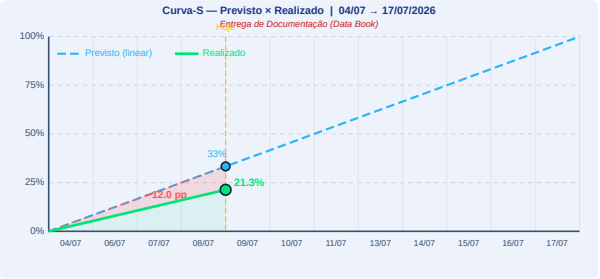

CARD 01 | Local 01

Junção ASU × CDC

33% | 2 concl. | 4 pend.

ANTES / LEVANTAMENTO

PÓS / REALIZADO

Foto Pós

Aguardando Conclusão

⊕ 23.1710S/46.9501W

◷ 15:14 — 02/07/2026

⊞ Av. Pref. Luís Latorre, 9600 — Setor Industrial, Jundiaí/SP

#	DISCIPLINA	ATIVIDADE / DESCRIÇÃO	PESO	STATUS	CONCLUSÃO
1	Macrodrenagem	Desforma da Escada 1	1	Concluída	100%

#	DISCIPLINA	ATIVIDADE / DESCRIÇÃO	PESO	STATUS	CONCLUSÃO
2	Macrodrenagem	Recolocação da canaleta na Berma da escada	1	Concluída	100%
3	Macrodrenagem	Acabamento final da superfície da escada (nata de cimento)	1	Pendente	—
4	Terraplanagem	Recomposição do talude / recompactação do solo próximo à Escada 1	1	Pendente	—
5	Plantio de Grama	Plantio de grama na região da Escada 1	1	Pendente	—
6	Geral / 5S	Limpeza geral e reorganização da área	1	Pendente	—

CARD 02 Local 02 **Canaleta — Escada 1** 25% 1 concl. 3 pend.

ANTES / LEVANTAMENTO

PÓS / REALIZADO

Foto Pós

Aguardando Conclusão

⊕ 23.1710S/46.9501W

◷ 15:16 — 02/07/2026

⊞ Av. Pref. Luís Latorre, 9600 — Setor Industrial, Jundiaí/SP

#	DISCIPLINA	ATIVIDADE / DESCRIÇÃO	PESO	STATUS	CONCLUSÃO
1	Macrodrenagem	Recomposição do solo e compactação na região da canaleta de interligação	1	Concluída	100%

#	DISCIPLINA	ATIVIDADE / DESCRIÇÃO	PESO	STATUS	CONCLUSÃO
2	Macrodrenagem	Corte da crista do talude para padronização da Berma da calha	1	Pendente	—
3	Plantio de Grama	Plantio de grama da base até a crista do talude	1	Pendente	—
4	Geral / 5S	Limpeza geral e reorganização da área	1	Pendente	—

CARD 03 | Local 03

Talude / Berma / Platô — Portaria Provisória

67% | 6 concl. | 3 pend.

ANTES / LEVANTAMENTO

PÓS / REALIZADO

Foto Pós

Aguardando Conclusão

⊕ 23.1706S/46.9497W

◷ 15:34 — 02/07/2026

⊞ Av. Pref. Luís Latorre, 9600 — Setor Industrial, Jundiaí/SP

#	DISCIPLINA	ATIVIDADE / DESCRIÇÃO	PESO	STATUS	CONCLUSÃO
1	Terraplanagem	Recomposição do talude / compactação do platô	1	Concluída	100%

#	DISCIPLINA	ATIVIDADE / DESCRIÇÃO	PESO	STATUS	CONCLUSÃO
2	Plantio de Grama	Replantio de grama no talude (trecho com lacunas de solo exposto)	1	Pendente	—
3	Terraplanagem	Acerto do terreno superficial da Berma	1	Concluída	100%
4	Terraplanagem	Acerto do terreno superficial do platô	1	Concluída	100%
5	Macrodrenagem	Aterrar e compactar as laterais da canaleta da Berma	1	Concluída	100%
6	Macrodrenagem	Rejuntamento com argamassa mista (traço 1:3) nas canaletas	1	Concluída	100%
7	Macrodrenagem	Recolocação da placa de obra	1	Concluída	100%
8	Macrodrenagem	Remoção do excedente de terra do platô	1	Pendente	—
9	Geral / 5S	Limpeza geral e reorganização da área	1	Pendente	—

CARD 04 Local 04 **Área Perimetral da Escada 2** 22% 2 concl. 7 pend.

ANTES / LEVANTAMENTO

PÓS / REALIZADO

Foto Pós

Aguardando Conclusão

⊕ 23.1703S/46.9492W

◷ 15:51 — 02/07/2026

⊞ Rod. Dom Gabriel Paulino Bueno Couto, 2045 — Chácara Terra Nova, Jundiaí/SP

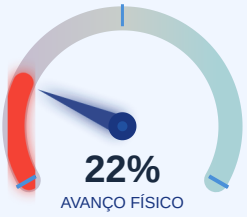

#	DISCIPLINA	ATIVIDADE / DESCRIÇÃO	PESO	STATUS	CONCLUSÃO
1	Terraplanagem	Acerto e aterro no platô abaixo da berma (laterais da Escada 2) com compactação	1	Pendente	0.0%

#	DISCIPLINA	ATIVIDADE / DESCRIÇÃO	PESO	STATUS	CONCLUSÃO
2	Macrodrenagem	Rejuntamento (traço 1:3) na canaleta da berma + compactação das laterais	1	Concluída	100%
3	Terraplanagem	Recomposição do talude / recompactação do solo em relação ao platô	1	Pendente	—
4	Macrodrenagem	Nivelamento do platô — canaleta: aterro, compactação e cimentação (traço 1:3)	1	Pendente	—
5	Plantio de Grama	Replantio de grama em toda a região perimetral da Escada 2	1	Pendente	—
6	Plantio de Grama	Replantio de grama nas laterais da escada e das canaletas	1	Pendente	—
7	Geral / 5S	Remoção do excedente de terra do platô	1	Pendente	—
8	Geral / 5S	Remoção das estacas de madeira	1	Concluída	100%
9	Geral / 5S	Limpeza geral e reorganização da área	1	Pendente	—

CARD 05 | Local 05

Talude em Curva — Escada 2

0% | 0 concl. | 4 pend.

ANTES / LEVANTAMENTO



PÓS / REALIZADO

Foto Pós

Aguardando Conclusão

⊕ 23.1703S/46.9492W

◷ 15:57 — 02/07/2026

⊞ Av. Pref. Luís Latorre, 9600 — Setor Industrial, Jundiaí/SP

#	DISCIPLINA	ATIVIDADE / DESCRIÇÃO	PESO	STATUS	CONCLUSÃO
1	Plantio de Grama	Remoção das placas de grama deslocadas do talude	1	Pendente	0.0%

#	DISCIPLINA	ATIVIDADE / DESCRIÇÃO	PESO	STATUS	CONCLUSÃO
2	Terraplanagem	Recomposição do solo e recompactação do talude	1	Pendente	—
3	Plantio de Grama	Replantio de grama em todo o talude em curva	1	Pendente	—
4	Geral / 5S	Limpeza geral e reorganização da área	1	Pendente	—

CARD 06 | Local 06 | **Superfície da Berma — Cota 691** | 33% | 1 concl. | 2 pend.

ANTES / LEVANTAMENTO

PÓS / REALIZADO

Foto Pós

Aguardando Conclusão

⊕ 23.1703S/46.9492W

◷ 16:00 — 02/07/2026

⊞ Av. Pref. Luís Latorre, 9600 — Setor Industrial, Jundiaí/SP

#	DISCIPLINA	ATIVIDADE / DESCRIÇÃO	PESO	STATUS	CONCLUSÃO
1	Macrodrenagem	Remoção de todo o solo excedente das atividades de macrodrenagem da Berma	1	Pendente	0.0%

#	DISCIPLINA	ATIVIDADE / DESCRIÇÃO	PESO	STATUS	CONCLUSÃO
2	Macrodrenagem	Remoção das sobras de canaleta e demais materiais residuais	1	Concluída	100%
3	Geral / 5S	Organização e limpeza geral da área da Berma (cota 691)	1	Pendente	—

CARD 07 | Local 06

Superfície da Berma — Cota 691

33% | 1 concl. | 2 pend.

ANTES / LEVANTAMENTO

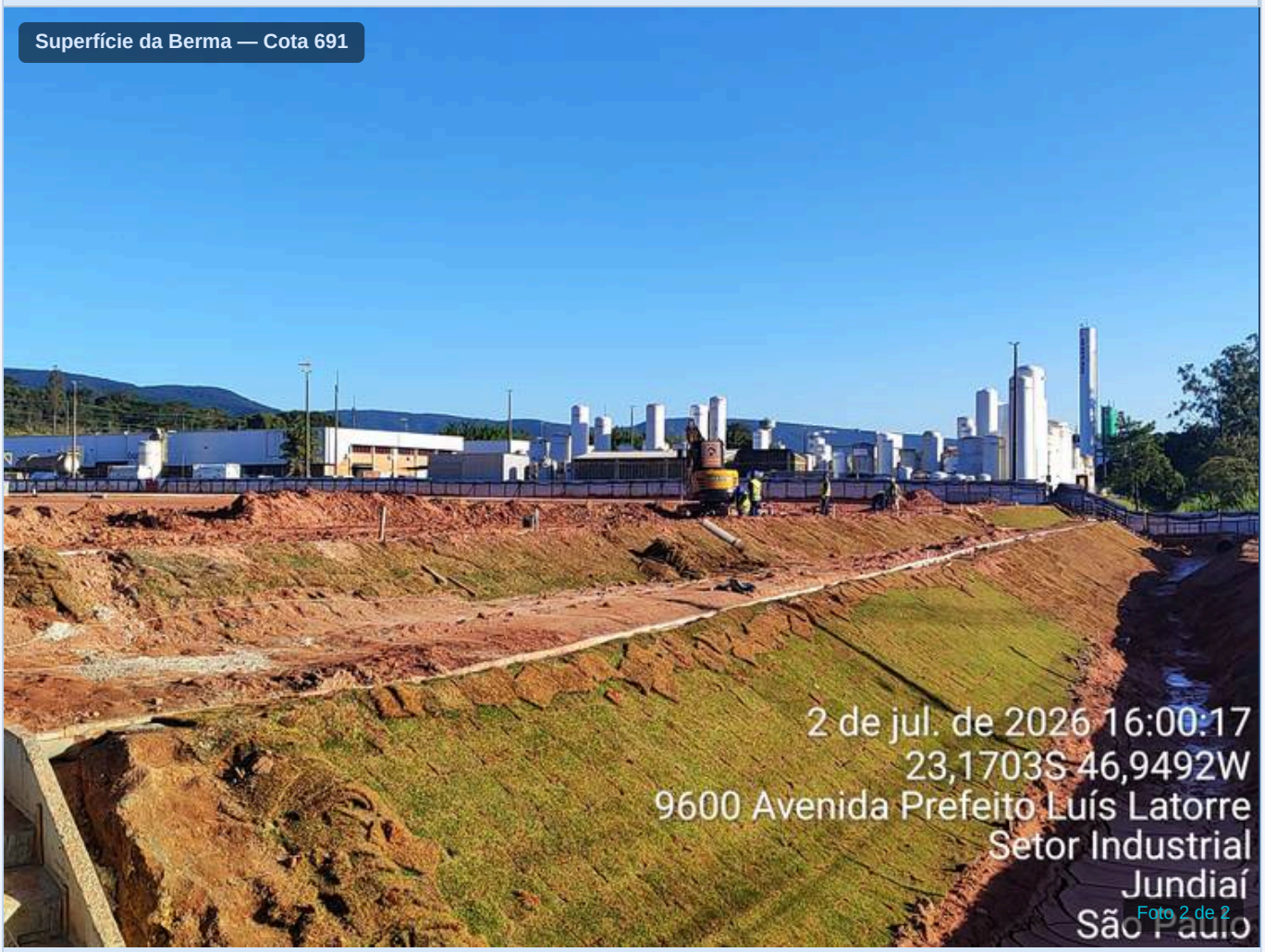

PÓS / REALIZADO

Foto Pós

Aguardando Conclusão

⊕ 23.1703S/46.9492W

◷ 16:00 — 02/07/2026

⊞ Av. Pref. Luís Latorre, 9600 — Setor Industrial, Jundiaí/SP

#	DISCIPLINA	ATIVIDADE / DESCRIÇÃO	PESO	STATUS	CONCLUSÃO
1	Macrodrenagem	Remoção de todo o solo excedente das atividades de macrodrenagem da Berma	1	Pendente	0.0%

#	DISCIPLINA	ATIVIDADE / DESCRIÇÃO	PESO	STATUS	CONCLUSÃO
2	Macrodrenagem	Remoção das sobras de canaleta e demais materiais residuais	1	Concluída	100%
3	Geral / 5S	Organização e limpeza geral da área da Berma (cota 691)	1	Pendente	—

CARD 08 Local 07 **Talude do Platô — Frente à Bacia** **75%** 3 concl. 1 pend.

ANTES / LEVANTAMENTO

PÓS / REALIZADO

Foto Pós

Aguardando Conclusão

⊕ 23.1702S/46.9491W

◷ 16:06 — 02/07/2026

⊞ Av. Pref. Luís Latorre, 9450–9600 — Setor Industrial, Jundiaí/SP

#	DISCIPLINA	ATIVIDADE / DESCRIÇÃO	PESO	STATUS	CONCLUSÃO
1	● Plantio de Grama	Replantio de toda a grama no talude do platô em frente à bacia	1	**Concluída**	100%

#	DISCIPLINA	ATIVIDADE / DESCRIÇÃO	PESO	STATUS	CONCLUSÃO
2	Geral / 5S	Remoção do entulho das canaletas	1	Concluída	100%
3	Geral / 5S	Remoção de madeira	1	Concluída	100%
4	Geral / 5S	Remoção de grama excedente e limpeza geral da área	1	Pendente	—

CARD 09 Local 08

Escada 3 — Portaria Definitiva do Projeto ASU 0%

0 concl. | 6 pend.

ANTES / LEVANTAMENTO

PÓS / REALIZADO

Foto Pós

Aguardando Conclusão

⊕ 23.1702S/46.9483W

◷ 16:14 — 02/07/2026

⊞ Rua Emílio Antonon, 1680 / Rua Nancy Carlota Netto, 120 — Jundiaí/SP

#	DISCIPLINA	ATIVIDADE / DESCRIÇÃO	PESO	STATUS	CONCLUSÃO
1	Macrodrenagem	Desforma da Escada 3	1	Pendente	0.0%

#	DISCIPLINA	ATIVIDADE / DESCRIÇÃO	PESO	STATUS	CONCLUSÃO
2	Macrodrenagem	Reaterro com compactação das faces laterais da Escada 3	1	Pendente	—
3	Macrodrenagem	Nivelamento com aterro na parte frontal da escada em relação à rua	1	Pendente	—
4	Macrodrenagem	Aplicação de argamassa superficial de regularização da Escada 3	1	Pendente	—
5	Plantio de Grama	Recomposição de grama nas áreas adjacentes à Escada 3	1	Pendente	—
6	Geral / 5S	Limpeza geral e remoção de entulho e resíduos de concretagem	1	Pendente	—

CARD 10 | Local 09 | **Canaleta da Berma — Curva da Bacia (Escad…** 0% | 0 concl. | 7 pend.

ANTES / LEVANTAMENTO

PÓS / REALIZADO

Foto Pós

Aguardando Conclusão

⊕ 23.1703S/46.9483W

◷ 16:17 — 02/07/2026

⊞ Rua Emílio Antonon, 1680 / Av. Pref. Luís Latorre, 2067 — Jundiaí/SP

#	DISCIPLINA	ATIVIDADE / DESCRIÇÃO	PESO	STATUS	CONCLUSÃO
1	Macrodrenagem	Remoção das canaletas da berma instaladas com problema de nivelamento	1	Pendente	0.0%

#	DISCIPLINA	ATIVIDADE / DESCRIÇÃO	PESO	STATUS	CONCLUSÃO
2	Macrodrenagem	Nivelamento superficial da base da vala da berma	1	Pendente	—
3	Macrodrenagem	Acerto do nível e compactação da Berma em relação à canaleta	1	Pendente	—
4	Macrodrenagem	Reinstalação das canaletas da berma com nivelamento correto	1	Pendente	—
5	Macrodrenagem	Impermeabilização interna das canaletas	1	Pendente	—
6	Macrodrenagem	Aplicação de argamassa de regularização (traço 1:3) nas canaletas	1	Pendente	—
7	Geral / 5S	Limpeza geral e remoção de entulho e resíduos da vala	1	Pendente	—

CARD 11 | Local 10 | **Talude da Bacia — Curva (Escada 3)** | 0% | 0 concl. | 4 pend.

ANTES / LEVANTAMENTO

PÓS / REALIZADO

Foto Pós

Aguardando Conclusão

⊕ 23.1703S/46.9483W

◷ 16:21 — 02/07/2026

⊞ Rua Emílio Antonon, 1680 — Chácara Aeroporto, Jundiaí/SP

#	DISCIPLINA	ATIVIDADE / DESCRIÇÃO	PESO	STATUS	CONCLUSÃO
1	Plantio de Grama	Remoção das gramas mal instaladas e deslocadas do talude	1	Pendente	0.0%

#	DISCIPLINA	ATIVIDADE / DESCRIÇÃO	PESO	STATUS	CONCLUSÃO
2	Terraplanagem	Nivelamento e compactação do solo do talude	1	Pendente	—
3	Plantio de Grama	Replantio de grama em todo o talude da curva da bacia	1	Pendente	—
4	Geral / 5S	Remoção de lona e resíduos do talude; limpeza geral da área	1	Pendente	—

CARD 12 | Local 10

Talude da Bacia — Curva (Escada 3)

0% | 0 concl. | 4 pend.

ANTES / LEVANTAMENTO

PÓS / REALIZADO

Foto Pós

Aguardando Conclusão

⊕ 23.1703S/46.9483W

◷ 16:21 — 02/07/2026

⊞ Rua Emílio Antonon, 1680 — Chácara Aeroporto, Jundiaí/SP

#	DISCIPLINA	ATIVIDADE / DESCRIÇÃO	PESO	STATUS	CONCLUSÃO
1	Plantio de Grama	Remoção das gramas mal instaladas e deslocadas do talude	1	Pendente	0.0%

#	DISCIPLINA	ATIVIDADE / DESCRIÇÃO	PESO	STATUS	CONCLUSÃO
2	Terraplanagem	Nivelamento e compactação do solo do talude	1	Pendente	—
3	Plantio de Grama	Replantio de grama em todo o talude da curva da bacia	1	Pendente	—
4	Geral / 5S	Remoção de lona e resíduos do talude; limpeza geral da área	1	Pendente	—

CARD 13 | Local 11 | **Berma Externa — Acompanhamento da Rua** | 0% | 0 concl. | 11 pend.

ANTES / LEVANTAMENTO

PÓS / REALIZADO

Foto Pós

Aguardando Conclusão

⊕ 23.1702–23.1715S/46.9479–46.9483W

◷ 16:25–16:30 — 02/07/2026

⊞ Av. Antonieta Piva Barranqueiros, 982 / Rua Nancy Carlota Netto, 120 — Jundiaí/SP

#	DISCIPLINA	ATIVIDADE / DESCRIÇÃO	PESO	STATUS	CONCLUSÃO
1	Macrodrenagem	Reaterro na face lateral da canaleta de 50cm	1	Pendente	0.0%

#	DISCIPLINA	ATIVIDADE / DESCRIÇÃO	PESO	STATUS	CONCLUSÃO
2	Macrodrenagem	Recompactação do solo nas laterais da canaleta	1	Pendente	—
3	Macrodrenagem	Limpeza interna da canaleta (remoção de sedimento acumulado)	1	Pendente	—
4	Macrodrenagem	Aplicação de argamassa de regularização (traço 1:3) nas juntas	1	Pendente	—
5	Macrodrenagem	Acerto no nivelamento da crista da Berma	1	Pendente	—
6	Macrodrenagem	Remoção da grama sobre pontos de subsidência e buracos na Berma	1	Pendente	—
7	Macrodrenagem	Recomposição do solo e nivelamento nos pontos de buraco/cavidade	1	Pendente	—
8	Macrodrenagem	Compactação do solo nos pontos recompostos	1	Pendente	—
9	Macrodrenagem	Replantio de grama na Berma e berma externa	1	Pendente	—
10	Macrodrenagem	Remoção do excedente de terra da berma	1	Pendente	—
11	Geral / 5S	Limpeza geral e organização da área	1	Pendente	—

CARD 14 | Local 11

Berma Externa — Acompanhamento da Rua

0% | 0 concl. | 11 pend.

ANTES / LEVANTAMENTO

PÓS / REALIZADO

Foto Pós

Aguardando Conclusão

⊕ 23.1702–23.1715S/46.9479–46.9483W

◷ 16:25–16:30 — 02/07/2026

⊞ Av. Antonieta Piva Barranqueiros, 982 / Rua Nancy Carlota Netto, 120 — Jundiaí/SP

#	DISCIPLINA	ATIVIDADE / DESCRIÇÃO	PESO	STATUS	CONCLUSÃO
1	Macrodrenagem	Reaterro na face lateral da canaleta de 50cm	1	Pendente	0.0%

#	DISCIPLINA	ATIVIDADE / DESCRIÇÃO	PESO	STATUS	CONCLUSÃO
2	Macrodrenagem	Recompactação do solo nas laterais da canaleta	1	Pendente	—
3	Macrodrenagem	Limpeza interna da canaleta (remoção de sedimento acumulado)	1	Pendente	—
4	Macrodrenagem	Aplicação de argamassa de regularização (traço 1:3) nas juntas	1	Pendente	—
5	Macrodrenagem	Acerto no nivelamento da crista da Berma	1	Pendente	—
6	Macrodrenagem	Remoção da grama sobre pontos de subsidência e buracos na Berma	1	Pendente	—
7	Macrodrenagem	Recomposição do solo e nivelamento nos pontos de buraco/cavidade	1	Pendente	—
8	Macrodrenagem	Compactação do solo nos pontos recompostos	1	Pendente	—
9	Macrodrenagem	Replantio de grama na Berma e berma externa	1	Pendente	—
10	Macrodrenagem	Remoção do excedente de terra da berma	1	Pendente	—
11	Geral / 5S	Limpeza geral e organização da área	1	Pendente	—

CARD 15 | Local 11 | **Berma Externa — Acompanhamento da Rua** | 0% | 0 concl. | 7 pend.

ANTES / LEVANTAMENTO

PÓS / REALIZADO

Foto Pós

Aguardando Conclusão

⊕ 23.1702–23.1715S/46.9479–46.9483W

◷ 16:25–16:30 — 02/07/2026

⊞ Av. Antonieta Piva Barranqueiros, 982 / Rua Nancy Carlota Netto, 120 — Jundiaí/SP

#	DISCIPLINA	ATIVIDADE / DESCRIÇÃO	PESO	STATUS	CONCLUSÃO
1	Macrodrenagem	Acerto no nivelamento da crista da Berma	1	Pendente	0.0%

#	DISCIPLINA	ATIVIDADE / DESCRIÇÃO	PESO	STATUS	CONCLUSÃO
2	Macrodrenagem	Remoção da grama sobre pontos de subsidência e buracos na Berma	1	Pendente	—
3	Macrodrenagem	Recomposição do solo e nivelamento nos pontos de buraco/cavidade	1	Pendente	—
4	Macrodrenagem	Compactação do solo nos pontos recompostos	1	Pendente	—
5	Macrodrenagem	Replantio de grama na Berma e berma externa	1	Pendente	—
6	Macrodrenagem	Remoção do excedente de terra da berma	1	Pendente	—
7	Geral / 5S	Limpeza geral e organização da área	1	Pendente	—

CARD 16 | Local 11

Berma Externa — Acompanhamento da Rua

18% | 2 concl. | 9 pend.

ANTES / LEVANTAMENTO

PÓS / REALIZADO

Foto Pós

Aguardando Conclusão

⊕ 23.1702–23.1715S/46.9479–46.9483W

◷ 16:25–16:30 — 02/07/2026

⊞ Av. Antonieta Piva Barranqueiros, 982 / Rua Nancy Carlota Netto, 120 — Jundiaí/SP

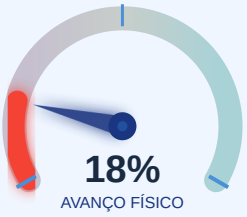

#	DISCIPLINA	ATIVIDADE / DESCRIÇÃO	PESO	STATUS	CONCLUSÃO
1	Macrodrenagem	Reaterro na face lateral da canaleta de 50cm	1	Pendente	0.0%

#	DISCIPLINA	ATIVIDADE / DESCRIÇÃO	PESO	STATUS	CONCLUSÃO
2	Macrodrenagem	Recompactação do solo nas laterais da canaleta	1	Pendente	—
3	Macrodrenagem	Limpeza interna da canaleta (remoção de sedimento acumulado)	1	Pendente	—
4	Macrodrenagem	Aplicação de argamassa de regularização (traço 1:3) nas juntas	1	Pendente	—
5	Macrodrenagem	Acerto no nivelamento da crista da Berma	1	Pendente	—
6	Macrodrenagem	Remoção da grama sobre pontos de subsidência e buracos na Berma	1	Concluída	100%
7	Macrodrenagem	Recomposição do solo e nivelamento nos pontos de buraco/cavidade	1	Concluída	100%
8	Macrodrenagem	Compactação do solo nos pontos recompostos	1	Pendente	—
9	Macrodrenagem	Replantio de grama na Berma e berma externa	1	Pendente	—
10	Macrodrenagem	Remoção do excedente de terra da berma	1	Pendente	—
11	Geral / 5S	Limpeza geral e organização da área	1	Pendente	—

CARD 17 | Local 11 | **Berma Externa — Acompanhamento da Rua** | **29%** | 2 concl. | 5 pend.

ANTES / LEVANTAMENTO

PÓS / REALIZADO

Foto Pós

Aguardando Conclusão

⊕ 23.1702–23.1715S/46.9479–46.9483W

◷ 16:25–16:30 — 02/07/2026

⊞ Av. Antonieta Piva Barranqueiros, 982 / Rua Nancy Carlota Netto, 120 — Jundiaí/SP

#	DISCIPLINA	ATIVIDADE / DESCRIÇÃO	PESO	STATUS	CONCLUSÃO
1	Macrodrenagem	Acerto no nivelamento da crista da Berma	1	Pendente	0.0%

#	DISCIPLINA	ATIVIDADE / DESCRIÇÃO	PESO	STATUS	CONCLUSÃO
2	Macrodrenagem	Remoção da grama sobre pontos de subsidência e buracos na Berma	1	Concluída	100%
3	Macrodrenagem	Recomposição do solo e nivelamento nos pontos de buraco/cavidade	1	Pendente	—
4	Macrodrenagem	Compactação do solo nos pontos recompostos	1	Pendente	—
5	Macrodrenagem	Replantio de grama na Berma e berma externa	1	Concluída	100%
6	Macrodrenagem	Remoção do excedente de terra da berma	1	Pendente	—
7	Geral / 5S	Limpeza geral e organização da área	1	Pendente	—

CARD 18 | Local 11

Berma Externa — Acompanhamento da Rua

29% | 2 concl. | 5 pend.

ANTES / LEVANTAMENTO

PÓS / REALIZADO

Foto Pós

Aguardando Conclusão

⊕ 23.1702–23.1715S/46.9479–46.9483W

◷ 16:25–16:30 — 02/07/2026

⊞ Av. Antonieta Piva Barranqueiros, 982 / Rua Nancy Carlota Netto, 120 — Jundiaí/SP

#	DISCIPLINA	ATIVIDADE / DESCRIÇÃO	PESO	STATUS	CONCLUSÃO
1	Macrodrenagem	Acerto no nivelamento da crista da Berma	1	Pendente	0.0%

#	DISCIPLINA	ATIVIDADE / DESCRIÇÃO	PESO	STATUS	CONCLUSÃO
2	Macrodrenagem	Remoção da grama sobre pontos de subsidência e buracos na Berma	1	Pendente	—
3	Macrodrenagem	Recomposição do solo e nivelamento nos pontos de buraco/cavidade	1	Concluída	100%
4	Macrodrenagem	Compactação do solo nos pontos recompostos	1	Pendente	—
5	Macrodrenagem	Replantio de grama na Berma e berma externa	1	Concluída	100%
6	Macrodrenagem	Remoção do excedente de terra da berma	1	Pendente	—
7	Geral / 5S	Limpeza geral e organização da área	1	Pendente	—

CARD 19 | Local 11

Berma Externa — Acompanhamento da Rua

18% | 2 concl. | 9 pend.

ANTES / LEVANTAMENTO

PÓS / REALIZADO

Foto Pós

Aguardando Conclusão

⊕ 23.1702–23.1715S/46.9479–46.9483W

◷ 16:25–16:30 — 02/07/2026

⊞ Av. Antonieta Piva Barranqueiros, 982 / Rua Nancy Carlota Netto, 120 — Jundiaí/SP

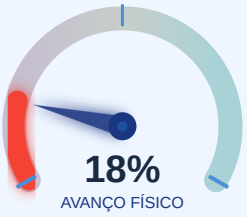

#	DISCIPLINA	ATIVIDADE / DESCRIÇÃO	PESO	STATUS	CONCLUSÃO
1	Macrodrenagem	Reaterro na face lateral da canaleta de 50cm	1	Pendente	0.0%

#	DISCIPLINA	ATIVIDADE / DESCRIÇÃO	PESO	STATUS	CONCLUSÃO
2	Macrodrenagem	Recompactação do solo nas laterais da canaleta	1	Pendente	—
3	Macrodrenagem	Limpeza interna da canaleta (remoção de sedimento acumulado)	1	Pendente	—
4	Macrodrenagem	Aplicação de argamassa de regularização (traço 1:3) nas juntas	1	Pendente	—
5	Macrodrenagem	Acerto no nivelamento da crista da Berma	1	Pendente	—
6	Macrodrenagem	Remoção da grama sobre pontos de subsidência e buracos na Berma	1	Concluída	100%
7	Macrodrenagem	Recomposição do solo e nivelamento nos pontos de buraco/cavidade	1	Pendente	—
8	Macrodrenagem	Compactação do solo nos pontos recompostos	1	Pendente	—
9	Macrodrenagem	Replantio de grama na Berma e berma externa	1	Concluída	100%
10	Macrodrenagem	Remoção do excedente de terra da berma	1	Pendente	—
11	Geral / 5S	Limpeza geral e organização da área	1	Pendente	—

CARD 20 | Local 11

Berma Externa — Acompanhamento da Rua

29% | 2 concl. | 5 pend.

ANTES / LEVANTAMENTO

PÓS / REALIZADO

Foto Pós

Aguardando Conclusão

⊕ 23.1702–23.1715S/46.9479–46.9483W

◷ 16:25–16:30 — 02/07/2026

⊞ Av. Antonieta Piva Barranqueiros, 982 / Rua Nancy Carlota Netto, 120 — Jundiaí/SP

#	DISCIPLINA	ATIVIDADE / DESCRIÇÃO	PESO	STATUS	CONCLUSÃO
1	Macrodrenagem	Acerto no nivelamento da crista da Berma	1	Pendente	0.0%

#	DISCIPLINA	ATIVIDADE / DESCRIÇÃO	PESO	STATUS	CONCLUSÃO
2	Macrodrenagem	Remoção da grama sobre pontos de subsidência e buracos na Berma	1	Concluída	100%
3	Macrodrenagem	Recomposição do solo e nivelamento nos pontos de buraco/cavidade	1	Pendente	—
4	Macrodrenagem	Compactação do solo nos pontos recompostos	1	Pendente	—
5	Macrodrenagem	Replantio de grama na Berma e berma externa	1	Concluída	100%
6	Macrodrenagem	Remoção do excedente de terra da berma	1	Pendente	—
7	Geral / 5S	Limpeza geral e organização da área	1	Pendente	—

CARD 21 | Local 11 | **Berma Externa — Acompanhamento da Rua** | **29%** | 2 concl. | 5 pend.

ANTES / LEVANTAMENTO



PÓS / REALIZADO

Foto Pós

Aguardando Conclusão

⊕ 23.1702–23.1715S/46.9479–46.9483W

◷ 16:25–16:30 — 02/07/2026

⊞ Av. Antonieta Piva Barranqueiros, 982 / Rua Nancy Carlota Netto, 120 — Jundiaí/SP

#	DISCIPLINA	ATIVIDADE / DESCRIÇÃO	PESO	STATUS	CONCLUSÃO
1	Macrodrenagem	Acerto no nivelamento da crista da Berma	1	Pendente	0.0%

#	DISCIPLINA	ATIVIDADE / DESCRIÇÃO	PESO	STATUS	CONCLUSÃO
2	Macrodrenagem	Remoção da grama sobre pontos de subsidência e buracos na Berma	1	Concluída	100%
3	Macrodrenagem	Recomposição do solo e nivelamento nos pontos de buraco/cavidade	1	Pendente	—
4	Macrodrenagem	Compactação do solo nos pontos recompostos	1	Pendente	—
5	Macrodrenagem	Replantio de grama na Berma e berma externa	1	Concluída	100%
6	Macrodrenagem	Remoção do excedente de terra da berma	1	Pendente	—
7	Geral / 5S	Limpeza geral e organização da área	1	Pendente	—

CARD 22 | Local 11

Berma Externa — Acompanhamento da Rua

29% | 2 concl. | 5 pend.

ANTES / LEVANTAMENTO

PÓS / REALIZADO

Foto Pós

Aguardando Conclusão

⊕ 23.1702–23.1715S/46.9479–46.9483W

◷ 16:25–16:30 — 02/07/2026

⊞ Av. Antonieta Piva Barranqueiros, 982 / Rua Nancy Carlota Netto, 120 — Jundiaí/SP

#	DISCIPLINA	ATIVIDADE / DESCRIÇÃO	PESO	STATUS	CONCLUSÃO
1	Macrodrenagem	Acerto no nivelamento da crista da Berma	1	Pendente	0.0%

#	DISCIPLINA	ATIVIDADE / DESCRIÇÃO	PESO	STATUS	CONCLUSÃO
2	Macrodrenagem	Remoção da grama sobre pontos de subsidência e buracos na Berma	1	Concluída	100%
3	Macrodrenagem	Recomposição do solo e nivelamento nos pontos de buraco/cavidade	1	Pendente	—
4	Macrodrenagem	Compactação do solo nos pontos recompostos	1	Pendente	—
5	Macrodrenagem	Replantio de grama na Berma e berma externa	1	Concluída	100%
6	Macrodrenagem	Remoção do excedente de terra da berma	1	Pendente	—
7	Geral / 5S	Limpeza geral e organização da área	1	Pendente	—

CARD 23 | Local 11

Berma Externa — Acompanhamento da Rua

18% | 2 concl. | 9 pend.

ANTES / LEVANTAMENTO

PÓS / REALIZADO

Foto Pós

Aguardando Conclusão

⊕ 23.1702–23.1715S/46.9479–46.9483W

◷ 16:25–16:30 — 02/07/2026

⊞ Av. Antonieta Piva Barranqueiros, 982 / Rua Nancy Carlota Netto, 120 — Jundiaí/SP

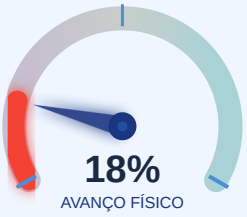

#	DISCIPLINA	ATIVIDADE / DESCRIÇÃO	PESO	STATUS	CONCLUSÃO
1	Macrodrenagem	Reaterro na face lateral da canaleta de 50cm	1	Pendente	0.0%

#	DISCIPLINA	ATIVIDADE / DESCRIÇÃO	PESO	STATUS	CONCLUSÃO
2	Macrodrenagem	Recompactação do solo nas laterais da canaleta	1	Pendente	—
3	Macrodrenagem	Limpeza interna da canaleta (remoção de sedimento acumulado)	1	Pendente	—
4	Macrodrenagem	Aplicação de argamassa de regularização (traço 1:3) nas juntas	1	Pendente	—
5	Macrodrenagem	Acerto no nivelamento da crista da Berma	1	Pendente	—
6	Macrodrenagem	Remoção da grama sobre pontos de subsidência e buracos na Berma	1	Concluída	100%
7	Macrodrenagem	Recomposição do solo e nivelamento nos pontos de buraco/cavidade	1	Pendente	—
8	Macrodrenagem	Compactação do solo nos pontos recompostos	1	Pendente	—
9	Macrodrenagem	Replantio de grama na Berma e berma externa	1	Concluída	100%
10	Macrodrenagem	Remoção do excedente de terra da berma	1	Pendente	—
11	Geral / 5S	Limpeza geral e organização da área	1	Pendente	—

CARD 24 | Local 12 | **Transição Berma × Platô — Final do Talude** | 0% | 0 concl. | 6 pend.

ANTES / LEVANTAMENTO

PÓS / REALIZADO

Foto Pós

Aguardando Conclusão

⊕ 23.1717S/46.9482W

◷ 16:37 — 02/07/2026

⊞ Rod. Dom Gabriel Paulino Bueno Couto, 11010 — Medeiros, Jundiaí/SP

#	DISCIPLINA	ATIVIDADE / DESCRIÇÃO	PESO	STATUS	CONCLUSÃO
1	Terraplanagem	Corte do aterro	1	Pendente	0.0%
2	Terraplanagem	Nivelamento do solo	1	Pendente	—

#	DISCIPLINA	ATIVIDADE / DESCRIÇÃO	PESO	STATUS	CONCLUSÃO
3	Terraplanagem	Compactação do solo	1	Pendente	—
4	Plantio de Grama	Plantio de grama	1	Pendente	—
5	Terraplanagem	Remoção de excedente de materiais	1	Pendente	—
6	Geral / 5S	Limpeza geral e reorganização da área	1	Pendente	—

CARD 25 | Local 13

Platô — Área de Tancagem

0% | 0 concl. | 3 pend.

ANTES / LEVANTAMENTO

PÓS / REALIZADO

Foto Pós

Aguardando Conclusão

⊕ 23.1718S/46.9481–46.9482W

◷ 16:42 — 02/07/2026

⊞ Rua Emílio Antonon, 1680 — Chácara Aeroporto, Jundiaí/SP

#	DISCIPLINA	ATIVIDADE / DESCRIÇÃO	PESO	STATUS	CONCLUSÃO
1	Terraplanagem	Aplicação de água com caminhão pipa	1	Pendente	0.0%
2	Terraplanagem	Nivelamento superficial da superfície	1	Pendente	—

#	DISCIPLINA	ATIVIDADE / DESCRIÇÃO	PESO	STATUS	CONCLUSÃO
3	Geral / 5S	Limpeza geral e reorganização da área	1	Pendente	—

CARD 26 | Local 13

Platô — Área de Tancagem

0% | 0 concl. | 3 pend.

ANTES / LEVANTAMENTO

PÓS / REALIZADO

Foto Pós

Aguardando Conclusão

⊕ 23.1718S/46.9481–46.9482W

◷ 16:42 — 02/07/2026

⊞ Rua Emílio Antonon, 1680 — Chácara Aeroporto, Jundiaí/SP

#	DISCIPLINA	ATIVIDADE / DESCRIÇÃO	PESO	STATUS	CONCLUSÃO
1	Terraplanagem	Aplicação de água com caminhão pipa	1	Pendente	0.0%
2	Terraplanagem	Nivelamento superficial da superfície	1	Pendente	—

#	DISCIPLINA	ATIVIDADE / DESCRIÇÃO	PESO	STATUS	CONCLUSÃO
3	Geral / 5S	Limpeza geral e reorganização da área	1	Pendente	—

CARD 27 | Local 13 | **Platô — Área de Tancagem** | 0% | 0 concl. | 3 pend.

ANTES / LEVANTAMENTO

PÓS / REALIZADO

Foto Pós

Aguardando Conclusão

⊕ 23.1718S/46.9481–46.9482W

◷ 16:42 — 02/07/2026

⊞ Rua Emílio Antonon, 1680 — Chácara Aeroporto, Jundiaí/SP

#	DISCIPLINA	ATIVIDADE / DESCRIÇÃO	PESO	STATUS	CONCLUSÃO
1	Terraplanagem	Aplicação de água com caminhão pipa	1	Pendente	0.0%
2	Terraplanagem	Nivelamento superficial da superfície	1	Pendente	—

#	DISCIPLINA	ATIVIDADE / DESCRIÇÃO	PESO	STATUS	CONCLUSÃO
3	Geral / 5S	Limpeza geral e reorganização da área	1	Pendente	—

CARD 28 | Local 14

Talude do Fundo da Obra

67% | 4 concl. | 2 pend.

ANTES / LEVANTAMENTO



PÓS / REALIZADO

Foto Pós

Aguardando Conclusão

⊕ 23.1721–23.1722S/46.9480W

◷ 16:45 — 02/07/2026

⊞ Rua Emílio Antonon, 1680 / Rod. Dom Gabriel Paulino Bueno Couto, 11010 — Jundiaí/SP

67%
AVANÇO FÍSICO

#	DISCIPLINA	ATIVIDADE / DESCRIÇÃO	PESO	STATUS	CONCLUSÃO
1	Plantio de Grama	Realinhamento da grama	1	Concluída	100%
2	Plantio de Grama	Plantio de grama no pé do talude	1	Concluída	100%

#	DISCIPLINA	ATIVIDADE / DESCRIÇÃO	PESO	STATUS	CONCLUSÃO
3	Plantio de Grama	Remoção de gramas mal instaladas	1	Concluída	100%
4	Terraplanagem	Nivelamento do solo	1	Pendente	—
5	Plantio de Grama	Replantio das gramas mal instaladas	1	Concluída	100%
6	Geral / 5S	Limpeza geral e reorganização da área	1	Pendente	—

CARD 29 | Local 14 | **Talude do Fundo da Obra** | **67%** | 4 concl. | 2 pend.

ANTES / LEVANTAMENTO

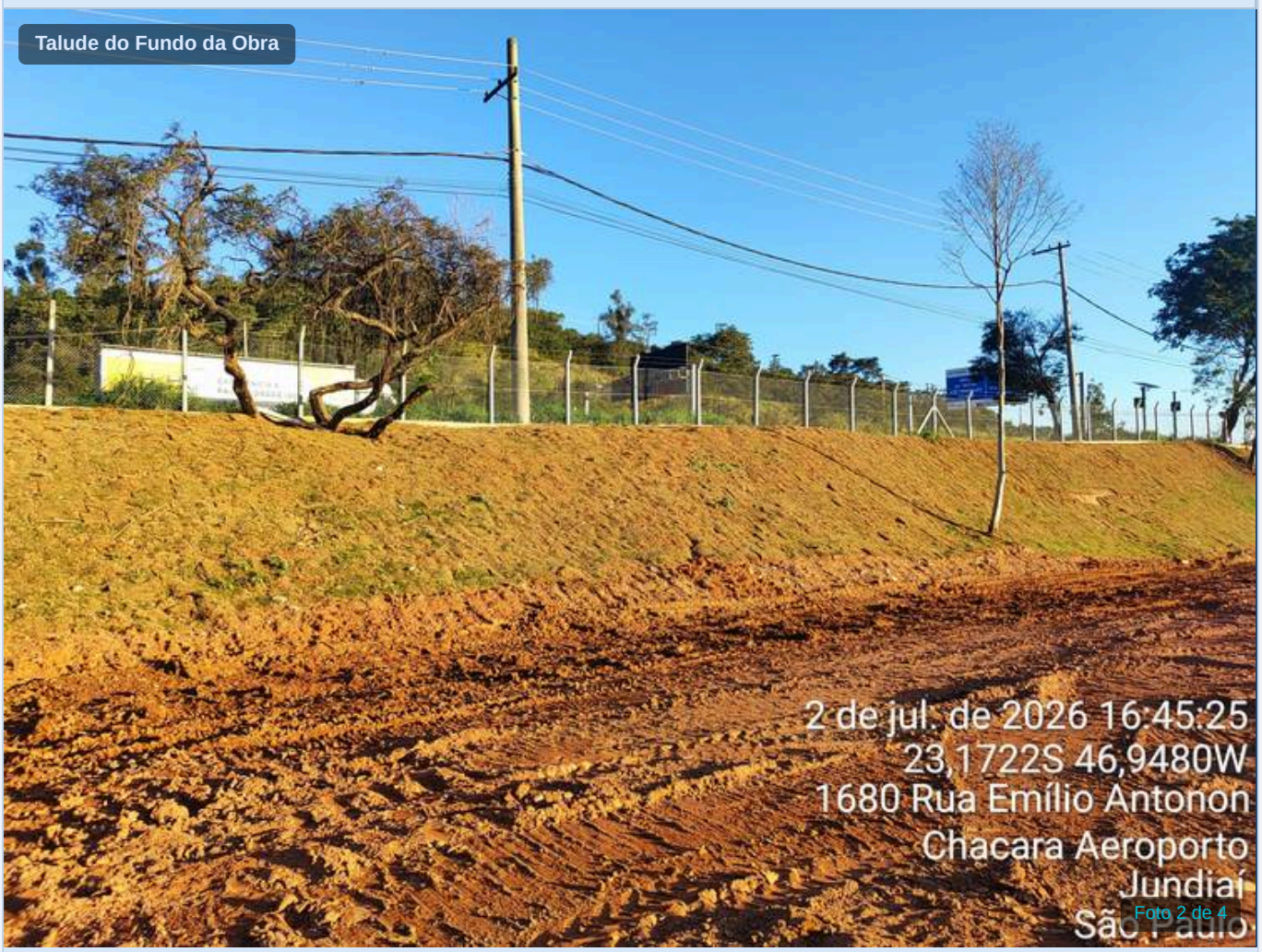

PÓS / REALIZADO

Foto Pós

Aguardando Conclusão

⊕ 23.1721–23.1722S/46.9480W

◷ 16:45 — 02/07/2026

⊞ Rua Emílio Antonon, 1680 / Rod. Dom Gabriel Paulino Bueno Couto, 11010 — Jundiaí/SP

67%
AVANÇO FÍSICO

#	DISCIPLINA	ATIVIDADE / DESCRIÇÃO	PESO	STATUS	CONCLUSÃO
1	Plantio de Grama	Realinhamento da grama	1	Concluída	100%
2	Plantio de Grama	Plantio de grama no pé do talude	1	Concluída	100%

#	DISCIPLINA	ATIVIDADE / DESCRIÇÃO	PESO	STATUS	CONCLUSÃO
3	Plantio de Grama	Remoção de gramas mal instaladas	1	Concluída	100%
4	Terraplanagem	Nivelamento do solo	1	Pendente	—
5	Plantio de Grama	Replantio das gramas mal instaladas	1	Concluída	100%
6	Geral / 5S	Limpeza geral e reorganização da área	1	Pendente	—

CARD 30 | Local 14

Talude do Fundo da Obra

67% | 4 concl. | 2 pend.

ANTES / LEVANTAMENTO



PÓS / REALIZADO

Foto Pós

Aguardando Conclusão

⊕ 23.1721–23.1722S/46.9480W

◷ 16:45 — 02/07/2026

⊞ Rua Emílio Antonon, 1680 / Rod. Dom Gabriel Paulino Bueno Couto, 11010 — Jundiaí/SP

67%
AVANÇO FÍSICO

#	DISCIPLINA	ATIVIDADE / DESCRIÇÃO	PESO	STATUS	CONCLUSÃO
1	Plantio de Grama	Realinhamento da grama	1	Concluída	100%
2	Plantio de Grama	Plantio de grama no pé do talude	1	Concluída	100%

#	DISCIPLINA	ATIVIDADE / DESCRIÇÃO	PESO	STATUS	CONCLUSÃO
3	Plantio de Grama	Remoção de gramas mal instaladas	1	Concluída	100%
4	Terraplanagem	Nivelamento do solo	1	Pendente	—
5	Plantio de Grama	Replantio das gramas mal instaladas	1	Concluída	100%
6	Geral / 5S	Limpeza geral e reorganização da área	1	Pendente	—

CARD 31 | Local 15

Platô — Frente ao Prédio Administrativo

0% | 0 concl. | 2 pend.

ANTES / LEVANTAMENTO

PÓS / REALIZADO

Foto Pós

Aguardando Conclusão

⊕ 23.1721S/46.9488W

◷ 16:51 — 02/07/2026

⊞ Rod. Dom Gabriel Paulino Bueno Couto, 11010 — Medeiros, Jundiaí/SP

0%
AVANÇO FÍSICO

#	DISCIPLINA	ATIVIDADE / DESCRIÇÃO	PESO	STATUS	CONCLUSÃO
1	Terraplanagem	Remoção de materiais espalhados	1	Pendente	0.0%
2	Geral / 5S	Limpeza geral e reorganização da área	1	Pendente	—

CARD 32 | Local 15

Platô — Frente ao Prédio Administrativo

0% | 0 concl. | 2 pend.

ANTES / LEVANTAMENTO

PÓS / REALIZADO

Foto Pós

Aguardando Conclusão

⊕ 23.1721S/46.9488W

◷ 16:51 — 02/07/2026

⊞ Rod. Dom Gabriel Paulino Bueno Couto, 11010 — Medeiros, Jundiaí/SP

#	DISCIPLINA	ATIVIDADE / DESCRIÇÃO	PESO	STATUS	CONCLUSÃO
1	Terraplanagem	Remoção de materiais espalhados	1	Pendente	0.0%
2	Geral / 5S	Limpeza geral e reorganização da área	1	Pendente	—

CARD 33 | Local 15

Platô — Frente ao Prédio Administrativo

0% | 0 concl. | 2 pend.

ANTES / LEVANTAMENTO



PÓS / REALIZADO

Foto Pós

Aguardando Conclusão

⊕ 23.1721S/46.9488W

◷ 16:51 — 02/07/2026

⊞ Rod. Dom Gabriel Paulino Bueno Couto, 11010 — Medeiros, Jundiaí/SP

#	DISCIPLINA	ATIVIDADE / DESCRIÇÃO	PESO	STATUS	CONCLUSÃO
1	Terraplanagem	Remoção de materiais espalhados	1	Pendente	0.0%
2	Geral / 5S	Limpeza geral e reorganização da área	1	Pendente	—

CARD 34 | Local 15

Platô — Frente ao Prédio Administrativo

0% | 0 concl. | 2 pend.

ANTES / LEVANTAMENTO

PÓS / REALIZADO

Foto Pós

Aguardando Conclusão

⊕ 23.1721S/46.9488W

◷ 16:51 — 02/07/2026

⊞ Rod. Dom Gabriel Paulino Bueno Couto, 11010 — Medeiros, Jundiaí/SP

0%
AVANÇO FÍSICO

#	DISCIPLINA	ATIVIDADE / DESCRIÇÃO	PESO	STATUS	CONCLUSÃO
1	Terraplanagem	Remoção de materiais espalhados	1	Pendente	0.0%
2	Geral / 5S	Limpeza geral e reorganização da área	1	Pendente	—

CARD 35 | Local 16

Platô Central

33% | 1 concl. | 2 pend.

ANTES / LEVANTAMENTO

PÓS / REALIZADO

Foto Pós

Aguardando Conclusão

⊕ 23.1712S/46.9491W – 23.1710S/46.9494W

◷ 09:36 — 03/07/2026

⊞ Rod. Dom Gabriel Paulino Bueno Couto, 11010 + Av. Pref. Luís Latorre, 9450 — Jundiaí/SP

33%
AVANÇO FÍSICO

#	DISCIPLINA	ATIVIDADE / DESCRIÇÃO	PESO	STATUS	CONCLUSÃO
1	Macrodrenagem	Remoção de Canaletas	1	Concluída	100%

#	DISCIPLINA	ATIVIDADE / DESCRIÇÃO	PESO	STATUS	CONCLUSÃO
2	Terraplanagem	Regularização e adensamento do Platôr Central	1	Pendente	—
3	Geral / 5S	Limpeza geral e reorganização da área	1	Pendente	—

CARD 36 | Local 16 | **Platô Central** | 0% | 0 concl. | 3 pend.

ANTES / LEVANTAMENTO



PÓS / REALIZADO

Foto Pós

Aguardando Conclusão

- 23.1712S/46.9491W – 23.1710S/46.9494W
- 09:36 — 03/07/2026
- Rod. Dom Gabriel Paulino Bueno Couto, 11010 + Av. Pref. Luís Latorre, 9450 — Jundiaí/SP

#	DISCIPLINA	ATIVIDADE / DESCRIÇÃO	PESO	STATUS	CONCLUSÃO
1	Macrodrenagem	Remoção de Canaletas	1	Pendente	0.0%

#	DISCIPLINA	ATIVIDADE / DESCRIÇÃO	PESO	STATUS	CONCLUSÃO
2	Terraplanagem	Regularização e adensamento do Platôr Central	1	Pendente	—
3	Geral / 5S	Limpeza geral e reorganização da área	1	Pendente	—

CARD 37 Local 16 **Platô Central** 33% 1 concl. 2 pend.

ANTES / LEVANTAMENTO

PÓS / REALIZADO

Foto Pós

Aguardando Conclusão

⊕ 23.1712S/46.9491W – 23.1710S/46.9494W

◷ 09:36 — 03/07/2026

⊞ Rod. Dom Gabriel Paulino Bueno Couto, 11010 + Av. Pref. Luís Latorre, 9450 — Jundiaí/SP

#	DISCIPLINA	ATIVIDADE / DESCRIÇÃO	PESO	STATUS	CONCLUSÃO
1	Macrodrenagem	Remoção de Canaletas	1	Concluída	100%

#	DISCIPLINA	ATIVIDADE / DESCRIÇÃO	PESO	STATUS	CONCLUSÃO
2	Terraplanagem	Regularização e adensamento do Platôr Central	1	Pendente	—
3	Geral / 5S	Limpeza geral e reorganização da área	1	Pendente	—

CARD 38 | Local C01

Caixa de Interligação 1

0% | 0 concl. | 1 pend.

ANTES / LEVANTAMENTO

PÓS / REALIZADO

Foto Pós

Aguardando Conclusão

⊕ —

◷ 07/07/2026

⊞ Av. Pref. Luís Latorre, 9450 — Setor Industrial, Jundiaí/SP

#	DISCIPLINA	ATIVIDADE / DESCRIÇÃO	PESO	STATUS	CONCLUSÃO
1	CFTV	Instalação da Tampa da Caixa de Interligação do Sistema de CFTV	1	Pendente	0.0%

CARD 39 | Local C02

Talude do Platô — Frente à Bacia

100% | 1 concl. | 0 pend.

ANTES / LEVANTAMENTO

PÓS / REALIZADO

Foto Pós

Aguardando Conclusão

⊕ —

◷ 07/07/2026

⊞ Rod. Dom Gabriel Paulino Bueno Couto, 6250 — Jundiaí/SP

#	DISCIPLINA	ATIVIDADE / DESCRIÇÃO	PESO	STATUS	CONCLUSÃO
1	● CFTV	Abertura de vala e enterramento do cabeamento do Sistema de CFTV	1	Concluída	100%

CARD 40 | Local C03

Talude do Platô — Frente à Bacia

50% | 1 concl. | 1 pend.

ANTES / LEVANTAMENTO



PÓS / REALIZADO

Foto Pós

Aguardando Conclusão

⊕ —

◷ 07/07/2026

⊞ Rod. Dom Gabriel Paulino Bueno Couto, 11010 — Medeiros, Jundiaí/SP

#	DISCIPLINA	ATIVIDADE / DESCRIÇÃO	PESO	STATUS	CONCLUSÃO
1	● CFTV	Abertura de vala e enterramento do cabeamento do Sistema de CFTV	1	Concluída	100%

#	DISCIPLINA	ATIVIDADE / DESCRIÇÃO	PESO	STATUS	CONCLUSÃO
2	● CFTV	Instalação da Tampa da Caixa de Interligação do Sistema de CFTV	1	Pendente	—

CARD 41 Local C04 **Caixa de Interligação 2** 0% 0 concl. 1 pend.

ANTES / LEVANTAMENTO

PÓS / REALIZADO

Foto Pós

Aguardando Conclusão

⊕ —

◷ 07/07/2026

⊞ Av. Pref. Luís Latorre, 9450 — Setor Industrial, Jundiaí/SP

#	DISCIPLINA	ATIVIDADE / DESCRIÇÃO	PESO	STATUS	CONCLUSÃO
1	● CFTV	Instalação da Tampa da Caixa de Interligação do Sistema de CFTV	1	Pendente	0.0%

CARD 42 | Local C05 | **Berma Externa — Acomp. da Rua — Frente …** **0%** | 0 concl. | 1 pend.

ANTES / LEVANTAMENTO

PÓS / REALIZADO

Foto Pós

Aguardando Conclusão

⊕ —

◷ 07/07/2026

⊞ Rod. Dom Gabriel Paulino Bueno Couto, 11010 — Medeiros, Jundiaí/SP

#	DISCIPLINA	ATIVIDADE / DESCRIÇÃO	PESO	STATUS	CONCLUSÃO
1	● CFTV	Abertura de vala, lançamento e enterramento do cabeamento do Sistema de CFTV	1	Pendente	0.0%

CARD 43 | Local C06 | **Caixa de Interligação 3** | 0% | 0 concl. | 1 pend.

ANTES / LEVANTAMENTO

PÓS / REALIZADO

Foto Pós

Aguardando Conclusão

⊕ —

◷ 07/07/2026

⊞ Rod. Dom Gabriel Paulino Bueno Couto, 6250 — Jundiaí/SP

#	DISCIPLINA	ATIVIDADE / DESCRIÇÃO	PESO	STATUS	CONCLUSÃO
1	● CFTV	Instalação da Tampa da Caixa de Interligação do Sistema de CFTV	1	Pendente	0.0%

CARD 44 Local C07 **Caixa de Interligação 4** 0% 0 concl. 1 pend.

ANTES / LEVANTAMENTO

PÓS / REALIZADO

Foto Pós

Aguardando Conclusão

⊕ —

◷ 07:45 — 07/07/2026

⊞ Av. Pref. Luís Latorre, 9450 — Setor Industrial, Jundiaí/SP

#	DISCIPLINA	ATIVIDADE / DESCRIÇÃO	PESO	STATUS	CONCLUSÃO
1	● CFTV	Instalação da Tampa da Caixa de Interligação do Sistema de CFTV	1	Pendente	0.0%

CARD 45 | Local C08

Talude / Berma / Platô — Portaria Provisória

0% | 0 concl. | 1 pend.

ANTES / LEVANTAMENTO

PÓS / REALIZADO

Foto Pós

Aguardando Conclusão

⊕ —

◷ 07:45 — 07/07/2026

⊞ Av. Pref. Luís Latorre, 9450 — Setor Industrial, Jundiaí/SP

#	DISCIPLINA	ATIVIDADE / DESCRIÇÃO	PESO	STATUS	CONCLUSÃO
1	● CFTV	Instalação da Tampa da Caixa de Interligação do Sistema de CFTV	1	Pendente	0.0%

CARD 46 | Local C09

Talude do Berma — Frente à Bacia

0% | 0 concl. | 3 pend.

ANTES / LEVANTAMENTO

PÓS / REALIZADO

Foto Pós

Aguardando Conclusão

⊕ —

◷ 07:34 — 07/07/2026

⊞ Rod. Dom Gabriel Paulino Bueno Couto, 11010 — Medeiros, Jundiaí/SP

#	DISCIPLINA	ATIVIDADE / DESCRIÇÃO	PESO	STATUS	CONCLUSÃO
1	CFTV	Abertura de vala e enterramento do cabeamento do Sistema de CFTV no talude	1	Pendente	0.0%

#	DISCIPLINA	ATIVIDADE / DESCRIÇÃO	PESO	STATUS	CONCLUSÃO
2	● CFTV	Finalização da instalação da caixa de passagem do Sistema de CFTV	1	Pendente	—
3	● CFTV	Instalação da Tampa da Caixa de Interligação do Sistema de CFTV	1	Pendente	—

CARD 47 | Local C10 | **Caixa de Interligação 5** | 0% | 0 concl. | 1 pend.

ANTES / LEVANTAMENTO

PÓS / REALIZADO

Foto Pós

Aguardando Conclusão

⊕ —

◷ 07:46 — 07/07/2026

⊞ Av. Pref. Luís Latorre, 9450 — Setor Industrial, Jundiaí/SP

#	DISCIPLINA	ATIVIDADE / DESCRIÇÃO	PESO	STATUS	CONCLUSÃO
1	● CFTV	Instalação da Tampa da Caixa de Interligação do Sistema de CFTV	1	Pendente	0.0%

CARD 48 | Local C11 | **Caixa de Interligação 6** | 0% | 0 concl. | 1 pend.

ANTES / LEVANTAMENTO

PÓS / REALIZADO

Foto Pós

Aguardando Conclusão

⊕ —

◷ 07/07/2026

⊞ —

#	DISCIPLINA	ATIVIDADE / DESCRIÇÃO	PESO	STATUS	CONCLUSÃO
1	● CFTV	Instalação da Tampa da Caixa de Interligação do Sistema de CFTV	1	Pendente	0.0%

CARD 49 | Local C12

Caixa de Interligação 7

0% | 0 concl. | 1 pend.

ANTES / LEVANTAMENTO

Caixa de Interligação 7

Foto não disponível

PÓS / REALIZADO

Foto Pós

Aguardando Conclusão

⊕ —

◷ 07:31 — 07/07/2026

⊞ Av. Marginal, 65 — Setor Industrial, Jundiaí/SP

#	DISCIPLINA	ATIVIDADE / DESCRIÇÃO	PESO	STATUS	CONCLUSÃO
1	CFTV	Instalação da Tampa da Caixa de Interligação do Sistema de CFTV	1	Pendente	0.0%